ประชาชน

สามารถออกแบบให้แสดงบทบาทว่าอยู่ในโหมดใดอย่างชัดเจน ?

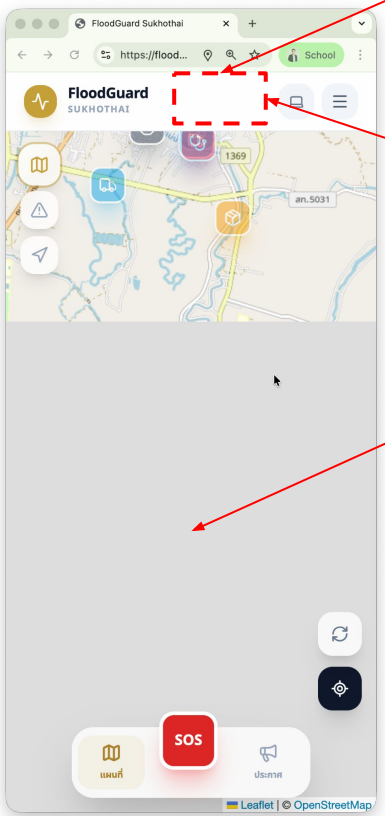

เพิ่มปุ่ม A+ , A- เพื่อเพิ่มลดตัวอักษร ที่ Navbar

on load ครั้งแรกแผนที่ขึ้นไม่ครบ ต้องกดที่ แผนที่ 1 ครั้งก่อน

ปุ่มแสดง Layer แผนที่

- ควรมีข้อความตอน Hover หรือ มีข้อความแสดงอยู่ด้านข้าง/ล่าง
- ปรับแปลี่ยน icon ตามรูปแนบโดยใช้ **สไตล์เดิม**

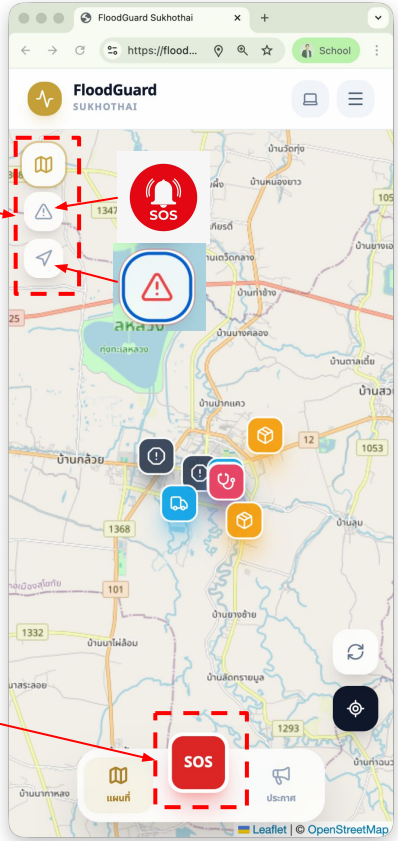



ให้เพิ่มเป็น 2 เมนู คือ

1. SOS เดิม โดยใช้เป็น Icon
   พร้อมมีข้อความด้านล่าง “ขอความช่วยเหลือ”
2. เพิ่มเมนูใหม่ โดยใช้ Icon
   พร้อมมีข้อความด้านล่าง
   “แจ้งเหตุ/จุดเสี่ยง”
   *** โดยทำเหมือนเจ้าหน้าที่ทุกอย่าง

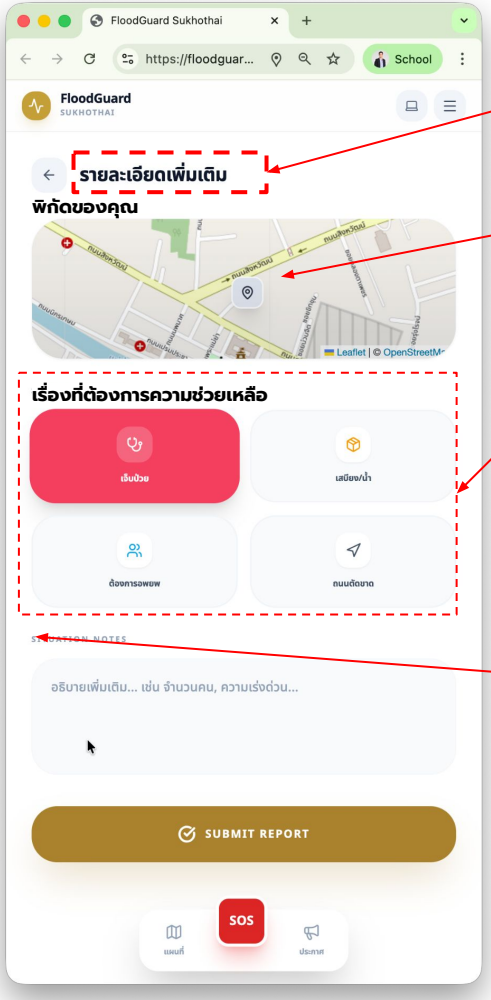



แก้เป็น “รายละเอียดขอความช่วยเหลือ”

เพิ่มชื่อหัวข้อ **“พิกัดของคุณ”** พร้อม ดึงที่อยู่ และ พิกัดมาแสดงใต้แผนที่
เช่น ต.ปากแคว อ.เมือง (GPS: 17.00, 99.80)
โดยแผนที่ให้ซูมในระดับมากที่สุด และไม่ให้เลื่อน

เพิ่มชื่อหัวข้อ **“เรื่องที่ต้องการความช่วยเหลือ”** โดยมี 4 หัวข้อให้เลือก คือ
1. ติดในบ้าน (น้ำสูงออกไม่ได้) 2. ขาดแคลนเสบียง 3. ต้องการอพยพ 4. มีผู้ป่วย/คนแก่/คนท้อง
พร้อมปรับ layout ให้ลด margin top/bottom ลงเพื่อให้ scroll น้อยที่สุด

เพิ่มหัวข้อ **มีผู้ประสบภัยกี่คน? (รวมตัวคุณ)** ในรูปแบบ Counter +/-

พร้อมมี Checkbox เพื่อบอกข้อมูล **[ ] มีผู้ป่วยติดเตียง / เคลื่อนย้ายลำบาก**

- เพิ่มหัวข้อสามารถแนบรูปถ่ายได้ 1 รูป
- เพิ่มการใส่เบอร์โทรศัพท์
- หมายเหตุยังไว้เหมือนเดิม
- คำว่า “submit report” เปลี่ยนเป็น “ส่งขอความช่วยเหลือ”



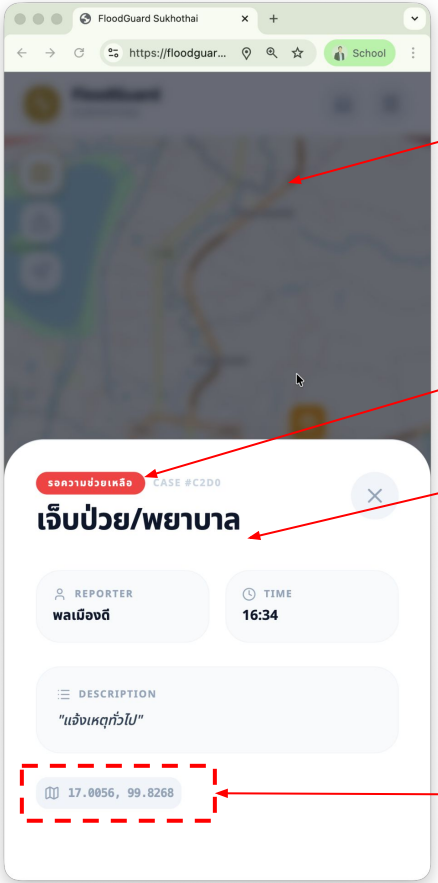

ไม่ต้องเบลอและสามารถเลื่อนตำแหน่งไปที่พิกัดที่ Click ได้หรือไหม

แสดงสถานะ OK แล้ว และควรปรับเปลี่ยนไปตามที่มีการอัพเดท เพิ่มขนาดตัวอักษรให้ใหญ่ขึ้น

แสดงข้อมูลตามหมวดหมู่ที่ถูกแจ้ง และปรับดึงข้อมูลตามที่แก้ในหน้าแจ้ง
โดยมีวันและเวลาที่แจ้ง

ปรับเป็นปุ่มนำทาง เพื่อเอาพิกัด ไปเปิดใน Google Map

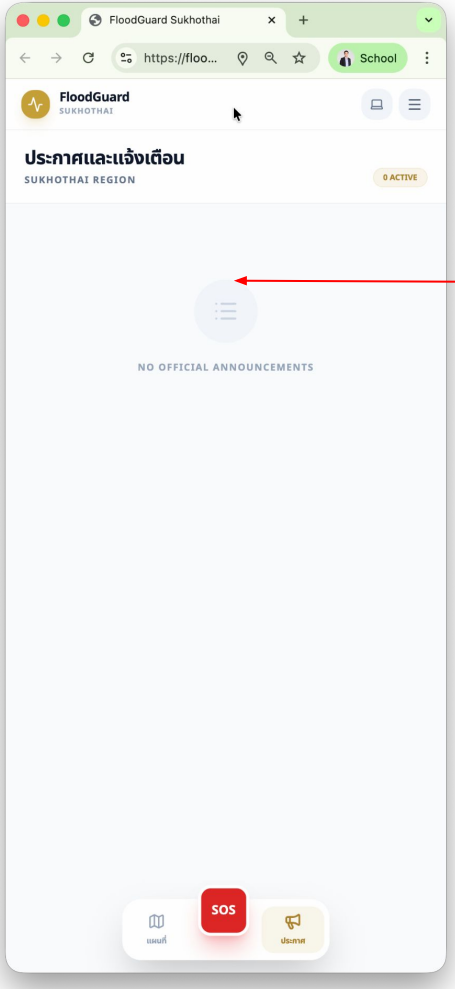

มีรายการที่ดึงข้อมูลจากประกาศ จากส่วน “ศูนย์บัญชาการ”
และเมื่อกดรายละเอียดจะเห็นรายละเอียดได้